FREE DOM

岡本 直也 様邸 新築工事 PLAN④

FREEDOM ARCHITECTS

2025/12/6

長期優良住宅

■仕様概要書

屋根仕上	ガルバリウム鋼板／縦ハゼ葺き	1F室内床	磁器質タイル600角
外壁仕上１	モルタル下地＋吹付塗装 通気層あり ジョリパット/アイカ	2F室内床1	カーペット敷
		2F室内床2	突板フローリング
断熱材	高性能グラスウール　等級５	内壁・天井	EP塗装/木目パネル貼
軒天仕上	アルテザート／神島化学工業	内建具	全てハイドア 一部ミラタップ クアドロスリム
ポーチ床	土間コンクリート金ゴテ	階段1～2F	鉄骨スケルトン階段 手摺／スチールフラットバー
テラス床	磁器質タイル 600角	階段2F～小屋裏	木製箱階段 木製てすり
バルコニー床	ポリカーボネート グレーチング	洗面台	造作洗面化粧台 アイカスマートサニタリー W2100　1ボウル 下部引き出し有、三面鏡、W1200
駐車場床	土間コンクリート金ゴテ		
建物外周部	砂利敷＋防草シート	トイレ	タンクレス
サッシ 防火	アルミ樹脂複合サッシ Lixil/防火FG-L/アルゴンガス入	キッチン	Ⅱ型　キッチンW2250 D900 コンロW2250 D650　食洗器
外周部　構造用合板	全周部　有	熱源	電気ガス併用／エコワン 70L
庇・軒先・ケラバ	軒ゼロ納まり 庇なし	浴室	１６１６サイズ
換気	第1種ダクトレス熱交換換気システム	床暖房	ガス温水式3マット
玄関外部	土間コンクリート金ゴテ	-	―

※排気ダクト有、給気ダクトレス
一種熱交換喚換気システム検討

■敷地概要・法的概要

住居表示	東京都世田谷区東玉川2丁目2-6
地名地番	東京都世田谷区東玉川二丁目11番2（2区画）
用途地域	第一種低層住居専用地域
防火指定	準防火地域
建蔽率	70%　※建蔽率緩和　角地＋準耐火：＋20%適用
容積率	100%　※指定容積率より
前面道路（北東側）	法第42条1項1号道路　幅員約3.8m　※敷地図より
前面道路（南東側）	法第42条1項1・5号道路 幅員約4.2m　※敷地図より
隣地斜線	20m+1.25L（住居系）
道路斜線	1.25L（住居系）
北側斜線	5m+1.25L（一低層・二低層）　※高度地区を優先とする
高度地区・絶対高さ	第一種高度地区　5m+0.6L　絶対高さ　10m
日影規制	4h-2.5h/1.5m　軒高7m超え又は地上3階建以上
埋蔵文化財	指定なし
盛土規制法	宅地造成等工事規制区域
中高層条例	軒高7m超え又は高さ8m超え又は地上3階建以上
景観計画	一般地域（低層住居系ゾーン）延べ面積1500㎡以上又は高さ10m以上
緑化地域	敷地面積150㎡以上
最低敷地面積	80㎡

■建物概要

主要用途	一戸建ての住宅	工事種別	新築
階数	地上2階建+小屋裏	工法	木造在来軸組工法
構造	準耐火構造		

■面積概要

敷地面積	88.08㎡			※分割図より	
許容建築面積	61.66㎡				
建築面積	49.79㎡	建蔽率	56.53%		OK
各階床面積					
1階	40.16㎡				
2階	49.79㎡				
ロフト階	13.00㎡				
延べ床面積	102.95㎡				
緩和：小屋裏	49.79㎡	×	1/2	24.90㎡	緩和面積　13.00㎡
緩和：地下(住宅部)	102.95㎡	×	1/3	34.32㎡	緩和面積
緩和：備蓄庫	102.95㎡	×	1/50	2.06㎡	緩和面積　2.06㎡
許容延べ床面積	88.08㎡		26.64坪		
容積対象床面積	87.89㎡	容積率	99.79%		OK

■施工床面積

1階	40.16㎡	12.15坪			
2階	49.79㎡	15.06坪	小屋裏（階段込み）	13.00㎡	3.93坪
			バルコニー	2.48㎡	0.75坪
			高天井1F	10.14㎡	3.07坪
			勾配天井2F	15.21㎡	4.60坪
計	89.95㎡	27.21坪	計	40.83㎡	12.35坪

※当社で提示した図面、資料等をFREEDOM株式会社の承諾なしに複製・転用を含む使用を禁じます。
※建築予定地の現場・役所調査が未了の場合、プラン変更が生じることがあります。
※所管行政庁、他の所轄行政機関、確認申請機関等の指導等によりプラン変更が生じることがあります。
※詳細な構造検討によりプラン変更が生じることがあります。
※敷地測量が未了の場合、測量結果によりプラン変更が生じることがあります。
※隣地境界より建物の離れが500mm以下の場合、民法第234条の規定により隣地所有者の方々に隣地近接承諾書へ署名捺印をいただく必要があります。
※敷地境界沿いの塀、フェンスは行政により改修指導がなされる場合があります。

公道法42条1項1号
道路幅員3.8m

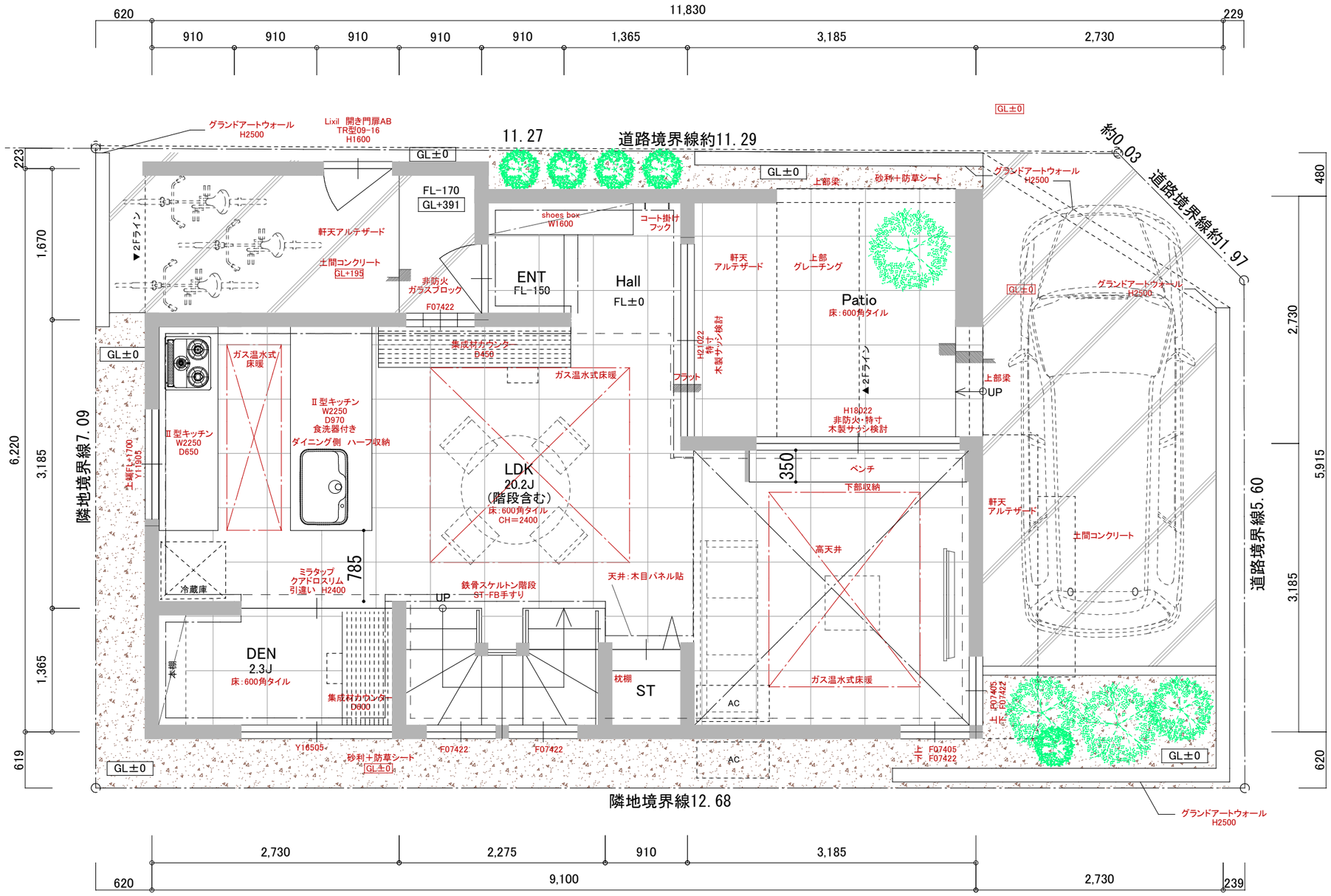

公道法42条1項1号
かつ
公道法42条1項5号
道路幅員4.2m

GL±0

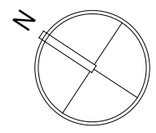

真北調査が必要です

※詳細な構造検討によりプラン変更が生じることがあります。
※敷地境界沿いの塀、フェンスは行政により改修指導がなされる場合があります。
※所管行政庁、他の所轄行政機関、確認申請機関等の指導等によりプラン変更が生じることがあります。
※隣地境界より建物の離れが 500mm以下の場合、民法第 234 条の規定により、隣地所有者に隣地近接承諾書へ署名捺印を頂く必要があります。

※当社で提示した図面、資料等をFREEDOM株式会社の承諾なしに複製・転用を含む使用を禁じます。
※建築予定地の現場調査、役所調査が未了の場合、プラン変更が生じることがあります。
※敷地測量が未了の場合、測量結果によりプラン変更が生じることがあります。

FREE DOM
FREEDOM ARCHITECTS
FREEDOM株式会社　自由が丘スタジオ一級建築士事務所
自由が丘スタジオ：一級　東京都知事登録　第59647号
東京都目黒区自由が丘2-10-14 青木ビル 2F　TEL:03-5731-8521

DATE HISTORY	PROJECT NUMBER	PROJECT TITLE	MANAGER	PLANNER	DRAWN BY	DRAWING TITLE	SHEET No
	202※-2※-※※※	岡本直也様邸新築工事	藤井	高橋	内田	1階平面図	A－1
			DATE 2025.12.6				SCALE 1 / 50

※この資料をFREEDOM株式会社の承諾なしに、複製、転用を含む使用を禁ず。行政の指導によりプラン変更の可能性があります。

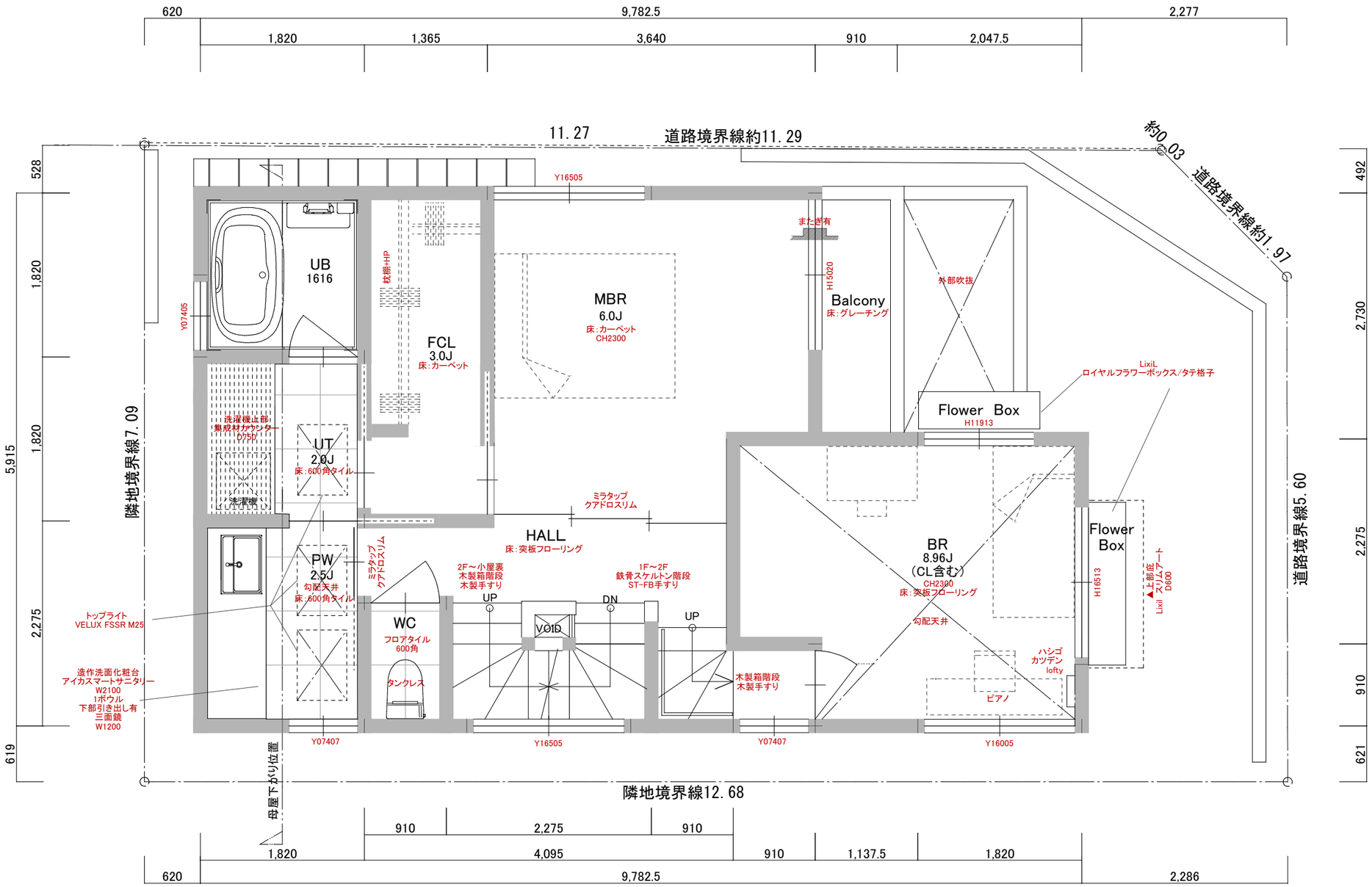

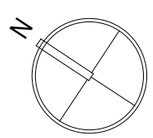

真北調査が必要です

※詳細な構造検討によりプラン変更が生じることがあります。
※敷地境界沿いの塀、フェンスは行政により改修指導がなされる場合があります。
※所管行政庁、他の所轄行政機関、確認申請機関等の指導等によりプラン変更が生じることがあります。
※隣地境界より建物の離れが 500mm以下の場合、民法第 234 条の規定により、隣地所有者に隣地近接承諾書へ署名捺印を頂く必要があります。

※当社で提示した図面、資料等をFREEDOM株式会社の承諾なしに複製・転用を含む使用を禁じます。
※建築予定地の現場調査、役所調査が未了の場合、プラン変更が生じることがあります。
※敷地測量が未了の場合、測量結果によりプラン変更が生じることがあります。

FREE DOM
FREEDOM ARCHITECTS
FREEDOM株式会社　自由が丘スタジオ一級建築士事務所
自由が丘スタジオ：一級　東京都知事登録　第59647号
東京都目黒区自由が丘2-10-14 青木ビル 2F　TEL:03-5731-8521

DATE HISTORY	PROJECT NUMBER	PROJECT TITLE	MANAGER	PLANNER	DRAWN BY	DRAWING TITLE	SHEET No
	202※-2※-※※※	岡本直也様邸新築工事	藤井	高橋	内田	2階平面図	A－2
			DATE 2025.12.6				SCALE 1 / 50

※この資料をFREEDOM株式会社の承諾なしに、複製、転用を含む使用を禁ず。行政の指導によりプラン変更の可能性があります。

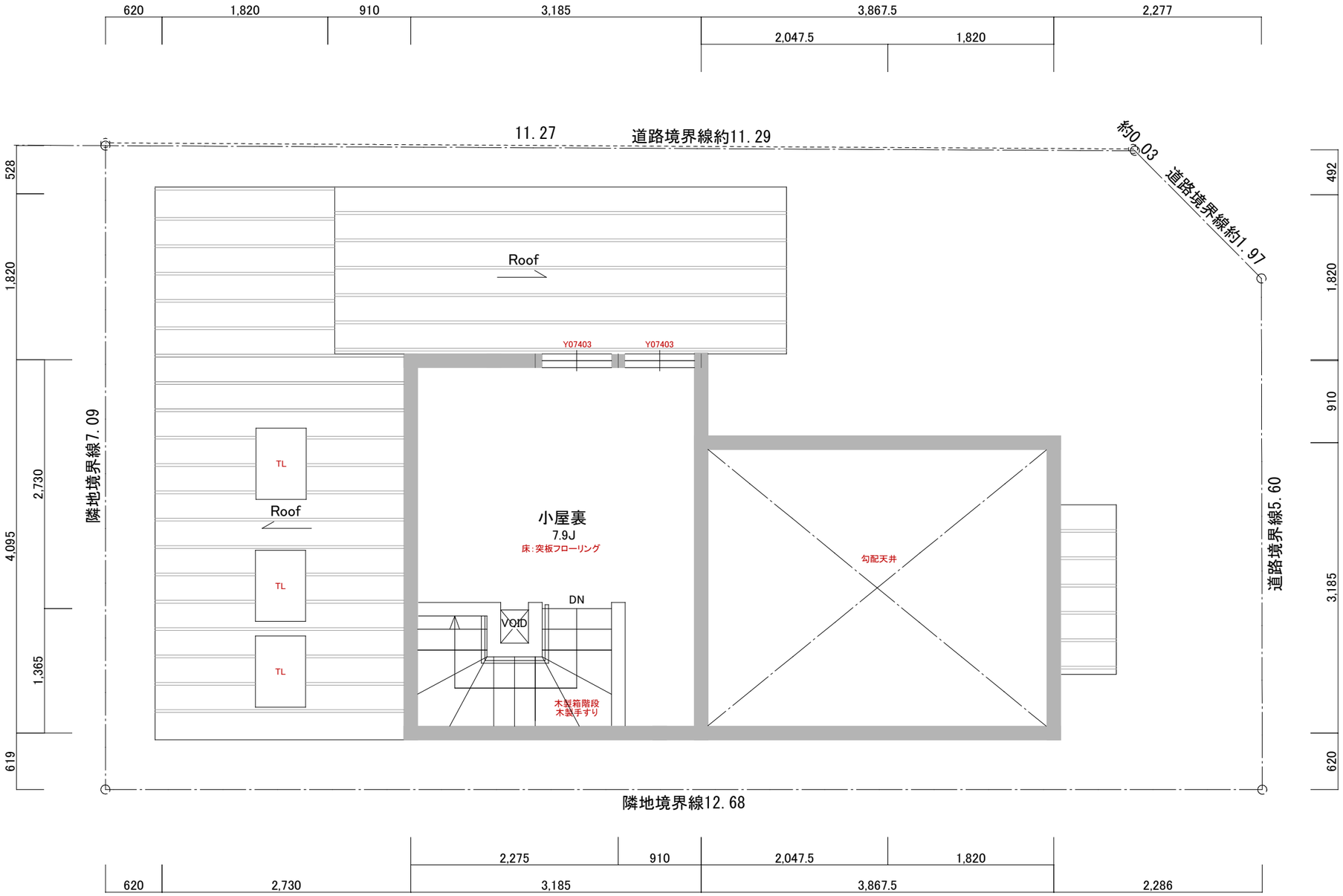

N

真北調査が必要です

※詳細な構造検討によりプラン変更が生じることがあります。
※敷地境界沿いの塀、フェンスは行政により改修指導がなされる場合があります。
※所管行政庁、他の所轄行政機関、確認申請機関等の指導等によりプラン変更が生じることがあります。
※隣地境界より建物の離れが 500mm以下の場合、民法第 234 条の規定により、隣地所有者に隣地近接承諾書へ署名捺印を頂く必要があります。

※当社で提示した図面、資料等をFREEDOM株式会社の承諾なしに複製・転用を含む使用を禁じます。
※建築予定地の現場調査、役所調査が未了の場合、プラン変更が生じることがあります。
※敷地測量が未了の場合、測量結果によりプラン変更が生じることがあります。

FREE DOM
FREEDOM ARCHITECTS
FREEDOM株式会社　自由が丘スタジオ一級建築士事務所
自由が丘スタジオ：一級　東京都知事登録　第59647号
東京都目黒区自由が丘2-10-14 青木ビル 2F　TEL:03-5731-8521

DATE HISTORY	PROJECT NUMBER	PROJECT TITLE	MANAGER	PLANNER	DRAWN BY	DRAWING TITLE	SHEET No
	202※-2※-※※※	岡本直也様邸新築工事	藤井	髙橋	内田	3階平面図	A－3
			DATE 2025.12.6				SCALE 1 / 50

※この資料をFREEDOM株式会社の承諾なしに、複製、転用を含む使用を禁ず。行政の指導によりプラン変更の可能性があります。

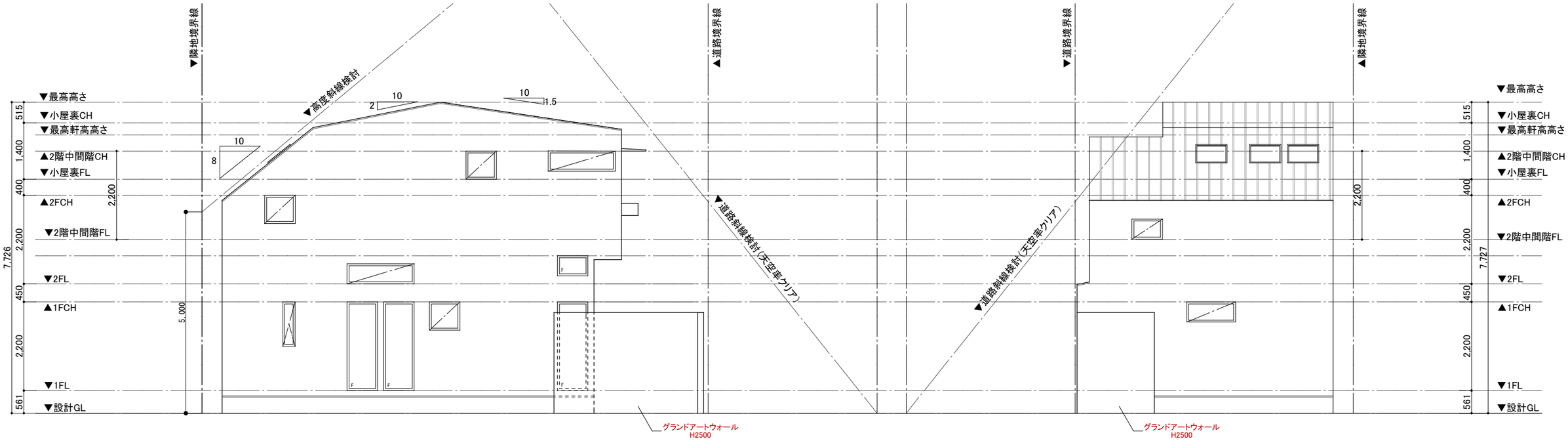

西立面図

北立面図

※詳細な構造検討によりプラン変更が生じることがあります。
※敷地境界沿いの塀、フェンスは行政により改修指導がなされる場合があります。
※所管行政庁、他の所轄行政機関、確認申請機関等の指導等によりプラン変更が生じることがあります。
※隣地境界より建物の離れが 500mm以下の場合、民法第 234 条の規定により、隣地所有者に隣地近接承諾書へ署名捺印を頂く必要があります。

※当社で提示した図面、資料等をFREEDOM株式会社の承諾なしに複製・転用を含む使用を禁じます。
※建築予定地の現場調査、役所調査が未了の場合、プラン変更が生じることがあります。
※敷地測量が未了の場合、測量結果によりプラン変更が生じることがあります。

FREE DOM
FREEDOM ARCHITECTS
FREEDOM株式会社　自由が丘スタジオ一級建築士事務所
自由が丘スタジオ：一級　東京都知事登録　第59647号
東京都目黒区自由が丘2-10-14 青木ビル 2F　TEL:03-5731-8521

DATE HISTORY	PROJECT NUMBER	PROJECT TITLE	MANAGER	PLANNER	DRAWN BY	DRAWING TITLE	SHEET No
	202※-2※-※※※	岡本様邸新築工事	藤井	高橋	内田	立面図	A－5
			DATE 2025.12.6				SCALE 1 / 100

※この資料をFREEDOM株式会社の承諾なしに、複製、転用を含む使用を禁ず。行政の指導によりプラン変更の可能性があります。

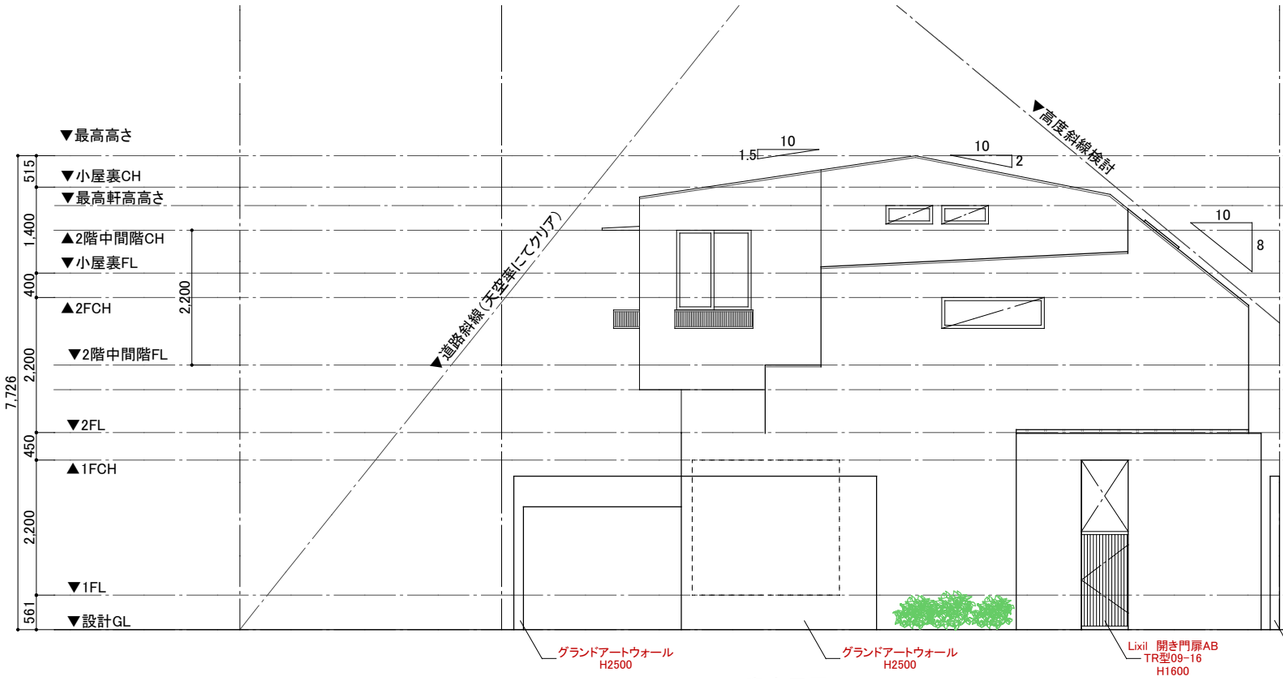

東立面図

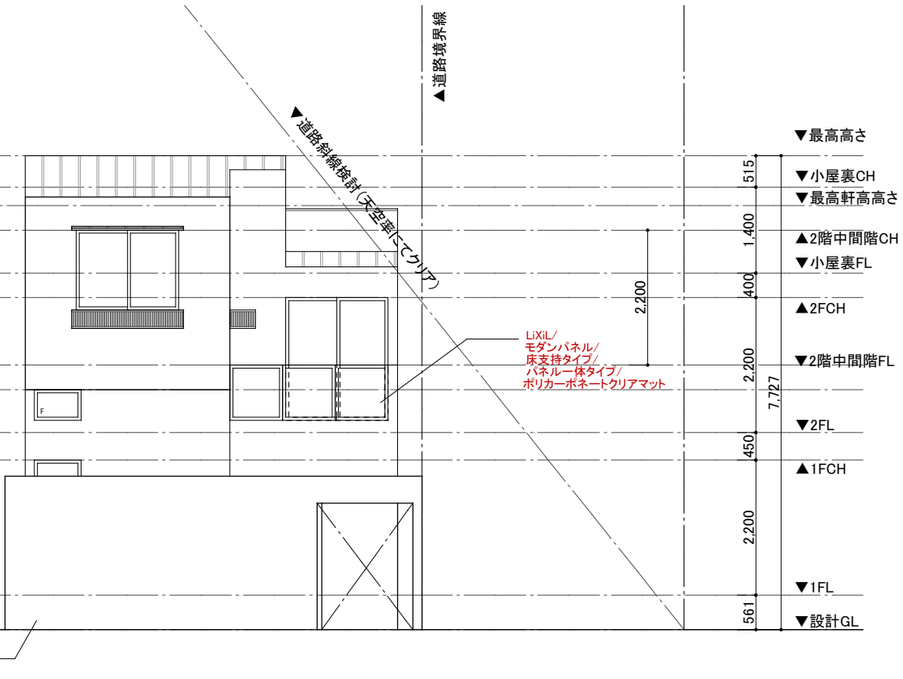

南立面図

※詳細な構造検討によりプラン変更が生じることがあります。
※敷地境界沿いの塀、フェンスは行政により改修指導がなされる場合があります。
※所管行政庁、他の所轄行政機関、確認申請機関等の指導等によりプラン変更が生じることがあります。
※隣地境界より建物の離れが 500mm以下の場合、民法第 234 条の規定により、隣地所有者に隣地近接承諾書へ署名捺印を頂く必要があります。

※当社で提示した図面、資料等をFREEDOM株式会社の承諾なしに複製・転用を含む使用を禁じます。
※建築予定地の現場調査、役所調査が未了の場合、プラン変更が生じることがあります。
※敷地測量が未了の場合、測量結果によりプラン変更が生じることがあります。

FREE DOM
FREEDOM ARCHITECTS
FREEDOM株式会社　自由が丘スタジオー級建築士事務所
自由が丘スタジオ：一級　東京都知事登録　第59647号
東京都目黒区自由が丘2-10-14 青木ビル 2F　TEL:03-5731-8521

DATE HISTORY	PROJECT NUMBER	PROJECT TITLE	MANAGER	PLANNER	DRAWN BY	DRAWING TITLE	SHEET No
	202※-2※-※※※	岡本様邸新築工事	藤井	髙橋	内田	立面図	A－4
			DATE 2025.12.6				SCALE 1 / 100

※この資料をFREEDOM株式会社の承諾なしに、複製、転用を含む使用を禁ず。行政の指導によりプラン変更の可能性があります。

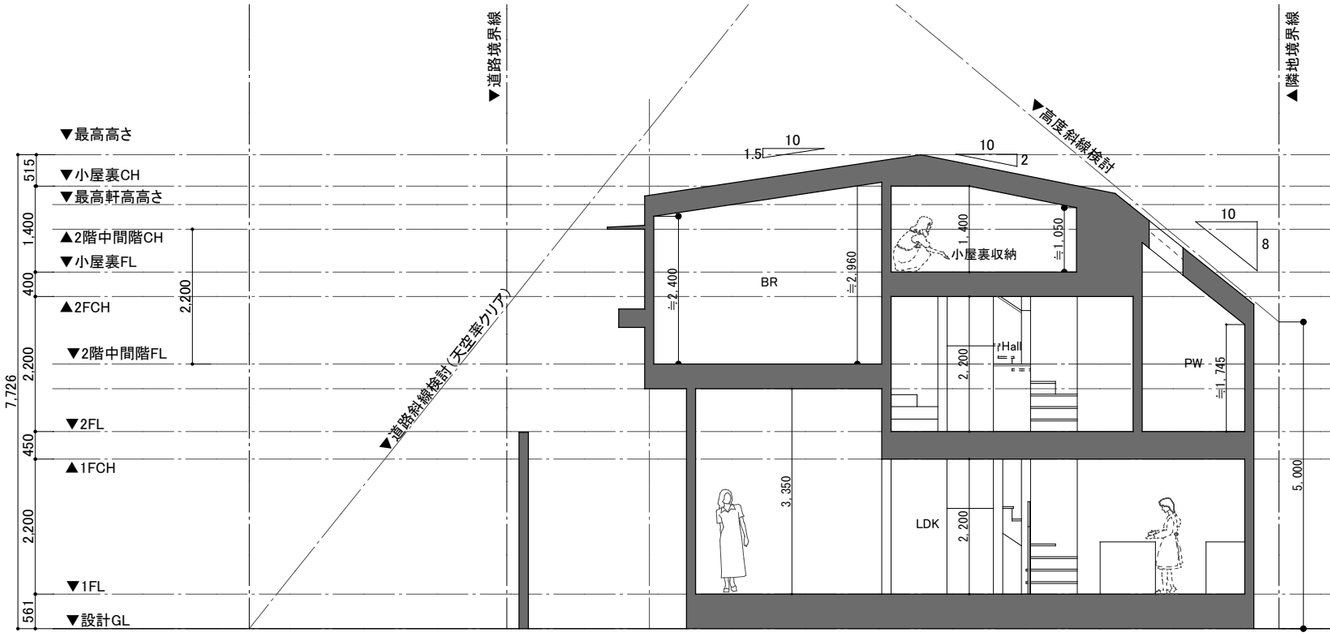

A－A'断面図

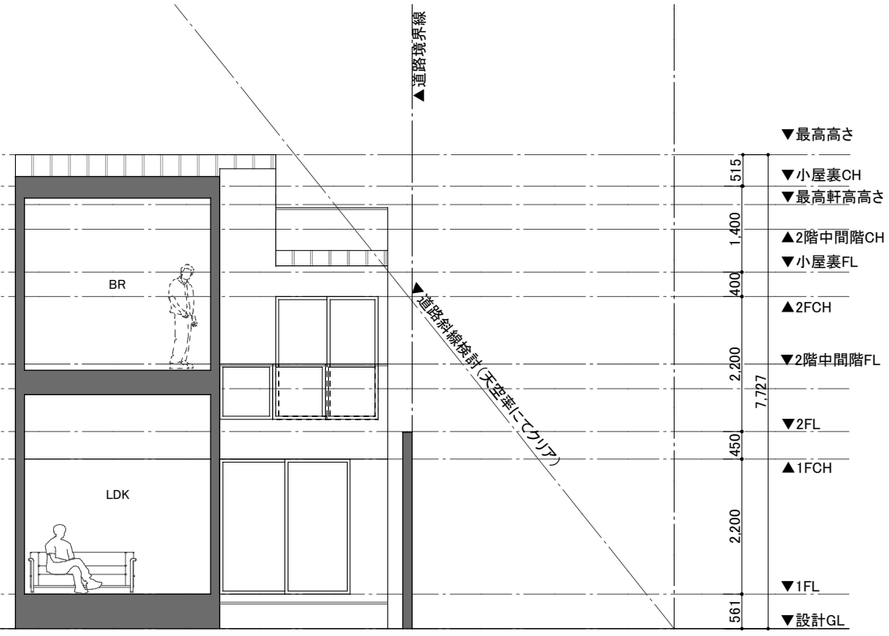

B－B'断面図

※詳細な構造検討によりプラン変更が生じることがあります。
※敷地境界沿いの塀、フェンスは行政により改修指導がなされる場合があります。
※所管行政庁、他の所轄行政機関、確認申請機関等の指導等によりプラン変更が生じることがあります。
※隣地境界より建物の離れが 500mm以下の場合、民法第 234 条の規定により、隣地所有者に隣地近接承諾書へ署名捺印を頂く必要があります。

※当社で提示した図面、資料等をFREEDOM株式会社の承諾なしに複製・転用を含む使用を禁じます。
※建築予定地の現場調査、役所調査が未了の場合、プラン変更が生じることがあります。
※敷地測量が未了の場合、測量結果によりプラン変更が生じることがあります。

FREE DOM
FREEDOM ARCHITECTS
FREEDOM株式会社　自由が丘スタジオ一級建築士事務所
自由が丘スタジオ：一級　東京都知事登録　第59647号
東京都目黒区自由が丘2-10-14 青木ビル 2F　TEL:03-5731-8521

DATE HISTORY	PROJECT NUMBER	PROJECT TITLE	MANAGER	PLANNER	DRAWN BY	DRAWING TITLE	SHEET No
	202※-2※-※※※	岡本様邸新築工事	冨谷	髙橋	内田	断面図	Ａ－6
			DATE 2025.12.6				SCALE 1 / 100

※この資料をFREEDOM株式会社の承諾なしに、複製、転用を含む使用を禁ず。行政の指導によりプラン変更の可能性があります。